HONDURAS 1:50,000

CORDILLERA ENTRE RÍOS

EDITION / EDICIÓN 1–DMA SERIES / SERIE E752 SHEET / HOJA 3058 II

One second of longitude equals 29.98m

One second of latitude equals 30.72m

CORDILLERA ENTRE RÍOS

HONDURAS

NICARAGUA

RÍO COCO (SEGOVIA) O WANGKI

Quita Espinazo

Cerro Wocken

Prepared and published by the Defense Mapping Agency Hydrographic/Topographic Center, Washington, D.C.

COMPILED IN 1985 FROM BEST AVAILABLE SOURCE MATERIALS
REDACCIÓN CARTOGRÁFICA HECHA EN 1985 DE LAS MEJORES FUENTES DISPONIBLES.

NOTES NOTAS

IN DEVELOPED AREAS ONLY THROUGH ROADS ARE CLASSIFIED.
EN LAS ÁREAS DESARROLLADAS, SOLAMENTE SE CLASIFICAN LAS VÍAS DIRECTAS.

A LANE ON THIS MAP IS CONSIDERED TO BE 2.5 METERS WIDE.
EN ESTE MAPA SE CONSIDERA QUE UNA VÍA TIENE 2.5 METROS DE ANCHURA.

CAUTION: NOT ALL TELEPHONE AND ELECTRIC SERVICE LINES ARE SHOWN.
ADVERTENCIA: NO SE MUESTRAN TODAS LAS LÍNEAS TELEFÓNICAS NI TODAS LAS LÍNEAS DE SERVICIO ELÉCTRICO

FIRST-ORDER ADMINISTRATIVE BOUNDARIES ARE APPROXIMATE
LOS LÍMITES DE DIVISIONES ADMINISTRATIVAS DE PRIMER ORDEN SON APROXIMATIVOS

GLOSSARY GLOSARIO

Caño	stream
Cordillera	mountain range
Río	river

CONVERSION GRAPH
GRÁFICO DE CONVERCIÓN
(1 meter = 3.28 feet)

Meters	Feet	Meters	Feet
900	2900	1600	5200
800	2600	1500	4900
700	2300	1400	4600
600	2000	1300	4300
500	1600	1200	3900
400	1300	1100	3600
300	1000	1000	3300
200	700	900	3000
100	400		

Scale 1:50,000

Meters 1000 500 0 1 2 3 4 5 Kilometers
1 ½ 0 1 2 3 Statute Miles
1 ½ 0 1 2 3 Nautical Miles

ELEVATIONS IN METERS

CONTOUR INTERVAL 20 METERS
SUPPLEMENTARY CONTOURS 10 METERS


INTERVALO DE CURVAS 20 METROS
CURVAS SUPLEMENTARIAS 10 METROS

SPHEROID	CLARKE 1866
GRID	1,000 METER UTM ZONE 16 (BLACK NUMBERED LINES) 1,000 METER LAMBERT, HONDURAS SOUTH ZONE (BLUE NUMBERED TICKS) 1,000 METER LAMBERT, NICARAGUA NORTH ZONE (BROWN NUMBERED TICKS)
PROJECTION	TRANSVERSE MERCATOR
VERTICAL DATUM	MEAN SEA LEVEL
HORIZONTAL DATUM	NORTH AMERICAN 1927

ESFERIODE	CLARKE 1866
CUADRÍCULA	TRANSVERSA DE MERCATOR A 1,000 METROS, ZONA 16 (LÍNEAS NEGRAS NUMERADAS) LAMBERT A 1,000 METROS, ZONA HONDURAS AL SUR (CIFRAS AZULES NUMERADAS) LAMBERT A 1,000 METROS, ZONA NICARAGUA AL NORTE (CIFRAS PARDAS NUMERADAS)
PROYECCIÓN	TRANSVERSA DE MERCATOR
DATO VERTICAL	NIVEL MEDIO DEL MAR
DATO HORIZONTAL	NORTE AMERICANO DE 1927

Reprinted by NIMA 02-99

SAMPLE 1,000 METER GRID SQUARE
EJEMPLO DEL CUADRADO DE 1,000 METROS



100,000 M. SQUARE IDENTIFICATION
IDENTIFICACIÓN DE CUADRÍCULA DE 100,000 METROS
FL

GRID ZONE DESIGNATION
DESIGNACIÓN DE ZONA DE CUADRÍCULA
16P

100 METER REFERENCE

1. Read large numbers labeling the VERTICAL grid line left of point and estimate tenths (100 meters) from grid line to point. 12 3
2. Read large numbers labeling the HORIZONTAL grid line below point and estimate tenths (100 meters) from grid line to point. 45 6

Example: 123456

WHEN REPORTING ACROSS A 100,000 METER LINE, PREFIX THE 100,000 METER SQUARE IDENTIFICATION IN WHICH THE POINT LIES.

Example: FL123456

WHEN REPORTING OUTSIDE THE GRID ZONE DESIGNATION AREA, PREFIX THE GRID ZONE DESIGNATION.

Example: 16PFL123456

REFERENCIA DE 100 METROS

1. Lleanse las cifras grandes correspondientes a la línea VERTICAL de la cuadrícula situada a la izquierda del punto y estímense los décimos (100 metros) entre la línea mencionada y el punto. 12 3
2. Lleanse las cifras grandes correspondientes a la línea HORIZONTAL de la cuadrícula situada debajo del punto y estímense los décimos (100 metros) entre la línea mencionada y el punto. 45 6

Ejemplo: 123456

CUANDO SE HACE REFERENCIA A UN PUNTO AL OTRO LADO DE UNA LÍNEA DE 100,000 METROS, ANTEPÓNGASE A LA REFERENCIA ANTERIOR LA IDENTIFICACIÓN DE LA CUADRÍCULA DE 100,000 METROS, DENTRO DEL CUAL SE ENCUENTRA EL PUNTO.

Ejemplo: FL123456

CUANDO SE HACE REFERENCIA FUERA DEL ÁREA DE LA ZONA DESIGNADA DE CUADRÍCULA ANTEPÓNGASE A LA REFERENCIA ANTERIOR LA DESIGNACIÓN DE LA ZONA DE CUADRÍCULA.

Ejemplo: 16PFL123456

USERS SHOULD REFER CORRECTIONS, ADDITIONS, AND COMMENTS TO THE NIMA CUSTOMER HELP DESK: 1-800-455-0899; COMMERCIAL: 1-314-260-5032; DSN 490-5032; OR WRITE TO: ATTN: COD, MAIL STOP P-37, NATIONAL IMAGERY AND MAPPING AGENCY, 4600 SANGAMORE ROAD, BETHESDA MD 20816-5003.

GRID NORTH
GRID MAGNETIC DECLINATION 3°00E
MAGNETIC NORTH

GRID CONVERGENCE 0°20' (6 MILS) FOR CENTER SHEET
CONVERGENCIA DE CUADRÍCULA 0°20'. (6 MILÉSIMAS) PARA EL CENTRO DE LA HOJA.

TO CONVERT A MAGNETIC AZIMUTH TO A GRID AZIMUTH ADD G-M ANGLE

TO CONVERT A GRID AZIMUTH TO A MAGNETIC AZIMUTH SUBTRACT G-M ANGLE

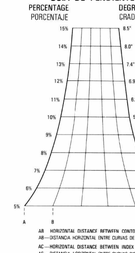
1985 G-M ANGLE 2° (-0 MILS)
ÁNGULO NCM DE 1985 2° (-0 MILÉSIMAS)

PARA CONVERTIR UN ACIMUT MAGNÉTICO A UN ACIMUT DE CUADRÍCULA SÚMESE EL ÁNGULO NC-M

PARA CONVERTIR UN ACIMUT DE CUADRÍCULA A UN ACIMUT MAGNÉTICO RÉSTESE EL ÁNGULO NC-M


SLOPE GUIDE
GUÍA DE PENDIENTES

PERCENTAGE PORCENTAJE — DEGREE GRADO



AB — HORIZONTAL DISTANCE BETWEEN CONTOURS
AB — DISTANCIA HORIZONTAL ENTRE CURVAS DE NIVEL
AC — HORIZONTAL DISTANCE BETWEEN INDEX CONTOURS
AC — DISTANCIA HORIZONTAL ENTRE CURVAS DIRECTRICES

BOUNDARIES
LÍMITES



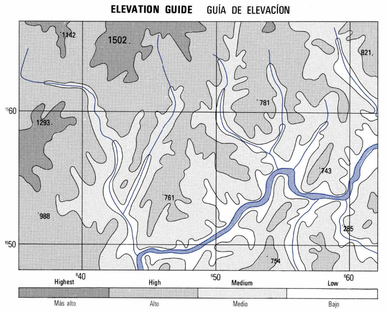
The representation of international boundaries is not necessarily authoritative

ADJOINING SHEETS
HOJAS ADYACENTES



Sheet 3058 II falls within NO 16-7, 1501, 1:250,000

ELEVATION GUIDE GUÍA DE ELEVACIÓN



THIS MAP IS RED-LIGHT READABLE

LEGEND
SIGNOS CONVENCIONALES

POBLACIONES

Densely built-up areas	Zonas edificadas de alta densidad
Sparsely to moderately built-up areas	Zonas edificadas de densidad moderada

CAMINOS

Divided highway	Autopista
All weather, hard surface	Para todo tiempo, carretera pavimentada
Two or more lanes wide	Dos omás vías; Una vía
One lane wide	Para todo tiempo, carretera
All weather, loose surface	mejorado; Dos o más
Two or more lanes wide	vías; Una vía
One lane wide	Camino transitable en
Fair or dry weather	verano
loose surface	Camino de herradura; Sendero
Track; Trail	Puente; Túnel
Bridge; Tunnel	Señales de ruta
Route marker: National; Secondary	Nacional; Secundaria

FERROCARRILES

Railroads (Single Una Vía / Multiple Dos Vías)	Vía normal
Normal gauge 1.067m.(3'6")	Vía estrecha
Narrow gauge .914m.(3')	Estación; Plato giratorio
Station; Turntable	

LÍMITES

International	Internacional
First-order administrative division (Departamento)	Primero-orden administrativo división
Cemetery; Native hut	Cementerio; Choza

Building; Church; School — Edificio; Iglesia; Escuela
Hospital; Located object — Hospital; Punto conspicuo
Watermill; Windmill, windpump — Molino de agua; Molino de viento, bomba de viento
Chimney; Tank; Fence — Chimenea; Tanque; Cerca
Mine; Active; Abandoned — Mina; Activa; Abandonada
Horizontal control point — Vértice geodésico
Bench mark — Punto fijo
Spot elevation in meters Highest; Normal — 287 285 — Punto elevación en metros Más alta; Normal
Power transmission line — Línea de transmisión
Telephone or telegraph line — Línea teléfono o telégrafo

RÍO

STREAMS — Perennial Río perenne — Intermittent Río intermitente

Less than 18m. wide	Menos de 18 metros de anchura
18m. to 25m. wide	18 metros a 25 metros de anchura
Over 25m. wide	Más de 25 metros de anchura
Spring; Well	Manantial; Pozo
Lake; Intermittent; dry	Lago; Intermitente; Seco
Dam; Masonry; Earthen	Presa; de mampostería; presa de tierra
Woodland 50% or more in crown cover, 3m. or more in height	Bosque-50% o más, de bosques de la corona 3 metros o mas de altura
Scrub-less than 3m. in height	Monte bajo-menos de 3 metros de anchura
Land subject to inundation	Terreno sujeto a inundacion
Scattered trees; Swamp	Arboles esparcidos; Pantano
Lava; Sand	Lava; Arena
Orchard; Vineyard	Huerta; Viña

CORDILLERA ENTRE RÍOS, HONDURAS ; NICARAGUA 3058 II E752 EDITION 1-DMA

LIMITED DISTRIBUTION: Distribution authorized to DoD IAW 10 U.S.C. §§130 & 2796. Release authorized to U.S. DoD contractors IAW 48 C.F.R. §252.245-7000. Refer other requests to Headquarters, NIMA, ATTN: Release Officer, Stop P-25. Destroy as "For Official Use Only". Removal of this caveat is prohibited.

NSN 7643014049234 ED. NO. 001
NIMA Ref No: E752X30582